חוק התכנון והבניה, התשכ"ה – 1965
תכנית מפורטת

מס' תמל\1016

שכונת הרקפות
באר-שבע

נספח נוסף	גליון 1	מתוך 1

מחוז	דרום
מרחב תכנון מקומי	באר שבע
רשות מקומית	באר שבע
יישוב	באר שבע
תאריך	27-11-2016
מהדורה	10
קנ"מ	1:200 15000

מגיש התכנית	שם	רשות מקרקעי ישראל	תפקיד
	תאגיד		
עורך התכנית	שם	נטמה פיש	תפקיד
	תאגיד		
יזם התכנית	שם	רשות מקרקעי ישראל	תפקיד
	תאגיד		
	שם	ניר הצפון	תפקיד
מודד	תאגיד		

בעלים	תאגיד	מדינת ישראל	תפקיד

מקרא

- גבול התוכנית
- גינה שכונתית
- גינה שכונתית משולבת באזורים אקסמפלריים מפוקפים
- שפחים אקסמפלריים מפוקפים
- אזורי אב-נטע
- נוף פתוח
- מיסעאות תוליכי רגל
- שביליים לאורך רחובות
- סיילת נופית
- המשך סיילת בשצ"פים
- קישוריות אל הנוף
- נקודות ציון נופיות בשולי התוכנית
- כיכר עירונית
- מגרש למבנה ציבור
- מגרש מסחרי
- כבשים
- רחוב משולב
- ציר נתיב
- עץ קשתמור
- עץ להתעתה
- עץ לעטירה
- נקי ענין מסקר מבע עירוני
- אתר ארכיאולוגי



השכד הירוק קנ"מ 1:2500



גינות שכונתיות משולבות באזורים אקסמפלריים מפוקפים

עקרונות התכנון הנופי

שימור שפחי מבע במחי מפוריש, בהתאם לערכי המבע הנריניים בשטח ועל פי מפרטי שמורה בשטח.

שימור וחזוקים בשחור שלחם כרכשות מבע עירוני.

שימור ראוי ושבשות ככוכ ציבורי – שמירה על מבשים רחוקים אל הפני השבוב.

שמחות צמחים ייחודיים ומחאים בשפחים המיועדים לבניה.

שילוב והשמה בין שפחים אקסמפלריים לשפחים האקסמפלריים.

השמחת מוכחות והציבור למערכת הרחוב.

יצירת מערכת רחוב המשכית של משפלים, רחובות, גינס אכוחנדים מיוחדים, תוך שמירה על עיני מבע ושמירות הצפיה במחשבי שם ושני ושחוח שבשני החיכרת.



אזור אב-נטע מזרחי

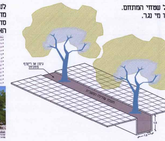
אזור אב-נטע מערבי

אזור אב-נטע מרכזי

מרבדי פריחה בגוש כובשים



בור שתילה בודד



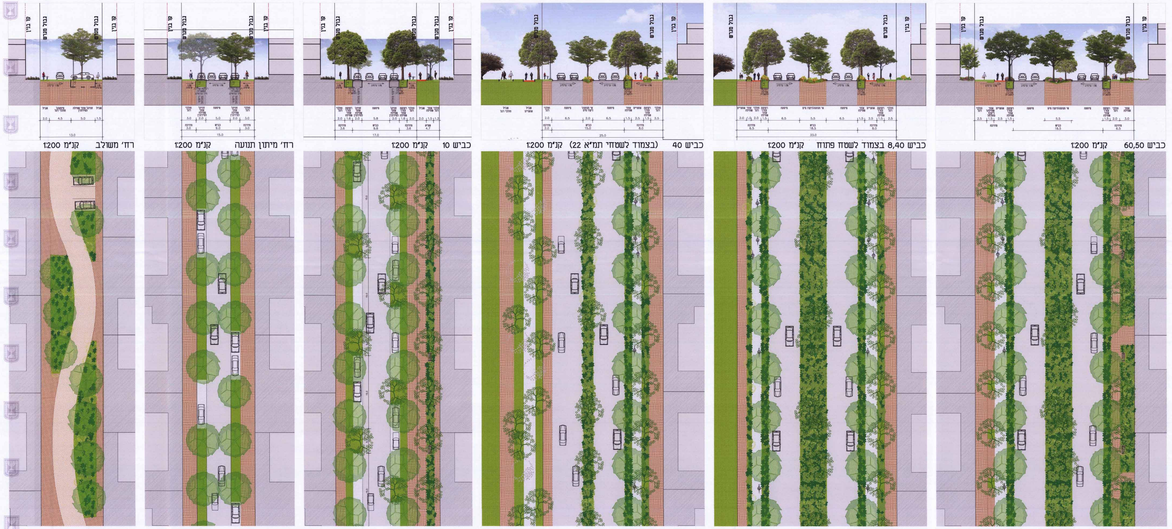
תעלת שתילה המשכית

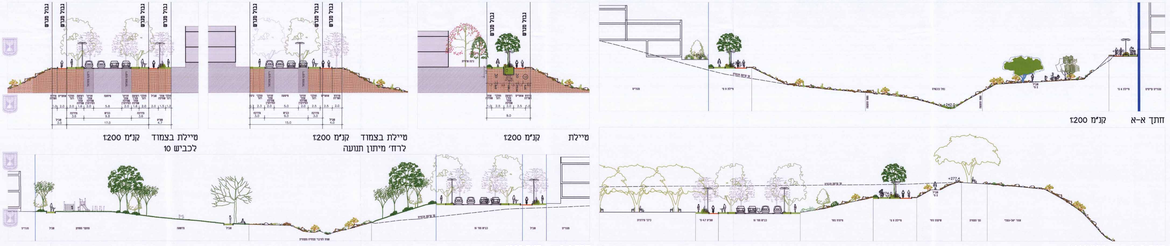


עצי רחוב מומלצים

לפשטות ברחובות "רבחו עצים מחי צל, מחאמי אקלים וחסכניים במים. מחלץ לשחשים נעצים מרחי שפרות.
מת עצי הרחוב יקבע מחוך רשימת עצי הרחוב המפויעה בחסכנית האסטמפצית קמחב וארבורי" שב באר שבע.

יש לשמוך על פירות פיזיולוגית שב בור ניחול, כשמפרט לוצן, בכב שמוך מחמחם.
בכב ניחון יחוז בור וביחול מחיבם ממלים וחצוים מחבבים וימנו מר טב.
יש לשחוף לבור ניחול רציפים בכב ניחון, ללא מחיצות.







ממשק אופיני בין שפחי המבע לשפחים המפותחים

גן שכונתי

רצועת נחל כובשים

מגרש פרטי